



PROTEZIONE CIVILE
Presidenza del Consiglio dei Ministri
Dipartimento della Protezione Civile

Bollettino di criticità n° 042/2026
Giorno di emissione: venerdì 6 febbraio 2026

BOLLETTINO DI CRITICITA' NAZIONALE - ALLERTA DEL 06/02/2026

Il **Centro Funzionale Centrale**, recepite le criticità comunicate dai Centri Funzionali Decentrati di tutte le Regioni e Province Autonome, **emette il bollettino di criticità nazionale / allerta**.

OGGI

Allerta meteo-idro arancione per oggi, venerdì 6 febbraio 2026

Consulta il bollettino per conoscere il livello e le zone di allerta sul tuo territorio

ALLERTA ARANCIONE METEO-IDRO



- ALLERTA ROSSA
- **ALLERTA ARANCIONE**
- ALLERTA GIALLA
- NESSUNA ALLERTA

DOMANI

Allerta meteo-idro gialla per domani, sabato 7 febbraio 2026

Consulta il bollettino per conoscere il livello e le zone di allerta sul tuo territorio

ALLERTA GIALLA METEO-IDRO



- ALLERTA ROSSA
- ALLERTA ARANCIONE
- **ALLERTA GIALLA**
- NESSUNA ALLERTA



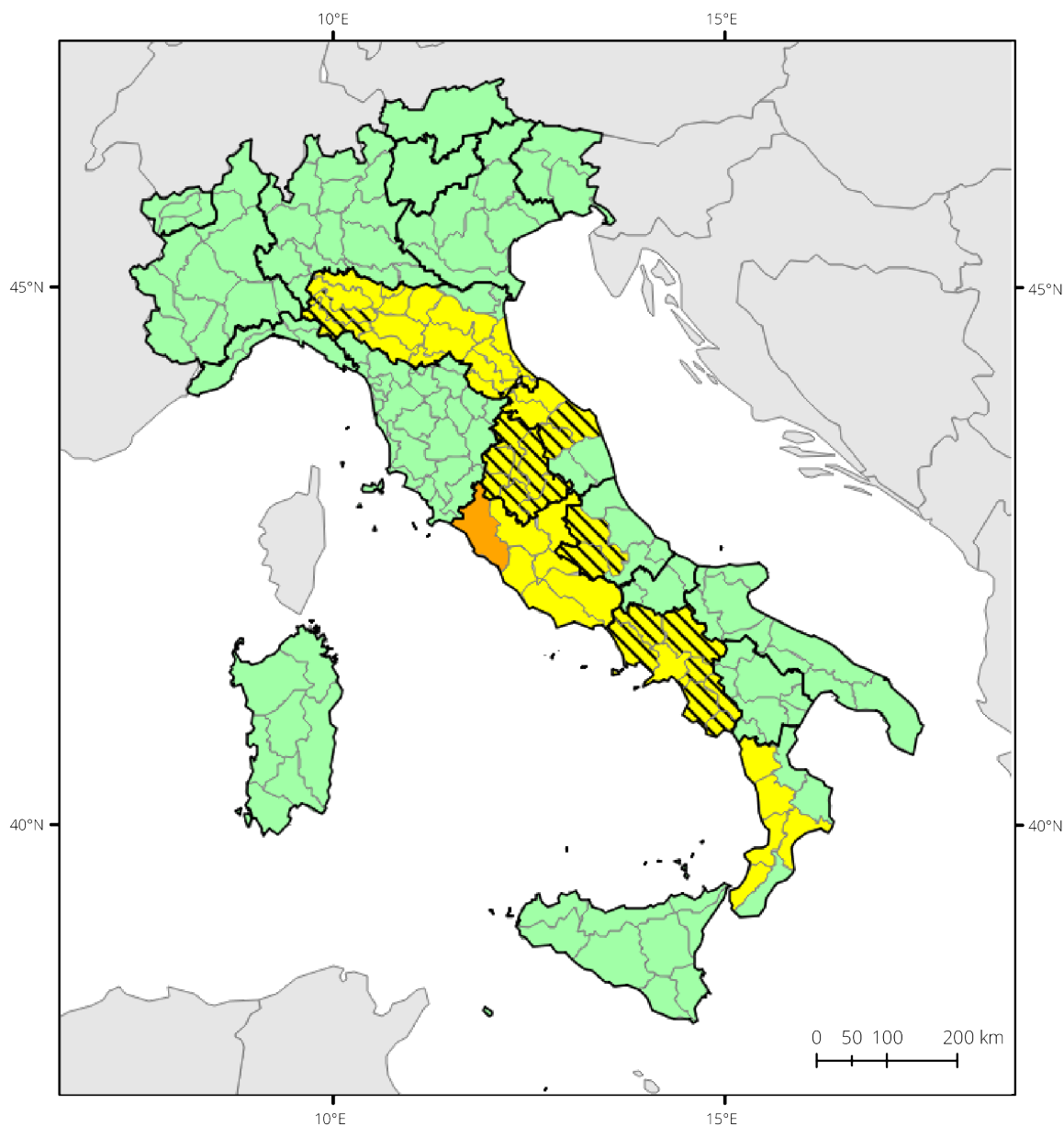
PROTEZIONE CIVILE
Presidenza del Consiglio dei Ministri
Dipartimento della Protezione Civile

Bollettino di criticità n° 042/2026
Giorno di emissione: venerdì 6 febbraio 2026

BOLLETTINO DI CRITICITA' NAZIONALE - ALLERTA DEL 06/02/2026

Effetti al suolo previsti per la giornata di oggi, venerdì 6 febbraio 2026

OGGI



LEGENDA DI CRITICITÀ

RISCHIO IDRAULICO

- ELEVATA CRITICITÀ
ALLERTA ROSSA
- MODERATA CRITICITÀ
ALLERTA ARANCIONE
- ORDINARIA CRITICITÀ
ALLERTA GIALLA

RISCHIO TEMPORALI

- MODERATA CRITICITÀ
ALLERTA ARANCIONE
- ORDINARIA CRITICITÀ
ALLERTA GIALLA

RISCHIO IDROGEOLOGICO

- ELEVATA CRITICITÀ
ALLERTA ROSSA
- MODERATA CRITICITÀ
ALLERTA ARANCIONE
- ORDINARIA CRITICITÀ
ALLERTA GIALLA

ASSENZA DI FENOMENI
NESSUNA ALLERTA

VALUTAZIONE NON
TRASMESSA

Regioni
Zone di allerta

Ufficio II - Attività Tecnico Scientifiche per la Previsione e Prevenzione dei Rischi



PROTEZIONE CIVILE
Presidenza del Consiglio dei Ministri
Dipartimento della Protezione Civile

Bollettino di criticità n° 042/2026
Giorno di emissione: venerdì 6 febbraio 2026

BOLLETTINO DI CRITICITA' NAZIONALE - ALLERTA DEL 06/02/2026

Effetti al suolo previsti per la giornata di oggi, venerdì 6 febbraio 2026



RISCHIO IDRAULICO

- ELEVATA CRITICITÀ
ALLERTA ROSSA
- MODERATA CRITICITÀ
ALLERTA ARANCIONE
- ORDINARIA CRITICITÀ
ALLERTA GIALLA
- ASSENZA DI FENOMENI
NESSUNA ALLERTA
- VALUTAZIONE NON
TRASMESSA
- Regioni
- Zone di allerta

NOTE:

nessuna



RISCHIO TEMPORALI

- MODERATA CRITICITÀ
ALLERTA ARANCIONE
- ORDINARIA CRITICITÀ
ALLERTA GIALLA
- ASSENZA DI FENOMENI
NESSUNA ALLERTA
- VALUTAZIONE NON
TRASMESSA
- Regioni
- Zone di allerta



RISCHIO IDROGEOLOGICO

- ELEVATA CRITICITÀ
ALLERTA ROSSA
- MODERATA CRITICITÀ
ALLERTA ARANCIONE
- ORDINARIA CRITICITÀ
ALLERTA GIALLA
- ASSENZA DI FENOMENI
NESSUNA ALLERTA
- VALUTAZIONE NON
TRASMESSA
- Regioni
- Zone di allerta

BOLLETTINO DI CRITICITA' NAZIONALE - ALLERTA DEL 06/02/2026

Effetti al suolo previsti per la giornata di oggi, venerdì 6 febbraio 2026

ELEVATA CRITICITÀ / ALLERTA ROSSA

PER RISCHIO IDRAULICO

Nessuna criticità

PER RISCHIO IDROGEOLOGICO

Nessuna criticità



MODERATA CRITICITÀ / ALLERTA ARANCIONE

PER RISCHIO IDRAULICO

Lazio: Lazi-A

PER RISCHIO TEMPORALI

Nessuna criticità

PER RISCHIO IDROGEOLOGICO

Nessuna criticità



ORDINARIA CRITICITÀ / ALLERTA GIALLA

PER RISCHIO IDRAULICO

Calabria: Cala-1, Cala-2, Cala-3, Cala-4, Cala-7

Campania: Camp-3

Emilia Romagna: Emil-A1, Emil-A2, Emil-B1, Emil-B2, Emil-C1, Emil-C2, Emil-D1, Emil-E1, Emil-E2, Emil-F1, Emil-F2, Emil-F3, Emil-H1, Emil-H2

Lazio: Lazi-B, Lazi-C, Lazi-D, Lazi-E, Lazi-F, Lazi-G

Marche: Marc-1, Marc-2


PER RISCHIO TEMPORALI

Calabria: Cala-1, Cala-2, Cala-3, Cala-4, Cala-7

PER RISCHIO IDROGEOLOGICO

Abruzzo: Abru-B, Abru-E

Calabria: Cala-1, Cala-2, Cala-3, Cala-4, Cala-7





PROTEZIONE CIVILE
Presidenza del Consiglio dei Ministri
Dipartimento della Protezione Civile

Bollettino di criticità n° 042/2026
Giorno di emissione: **venerdì 6 febbraio 2026**

Campania: Camp-1, Camp-2, Camp-3, Camp-4, Camp-5, Camp-6, Camp-7, Camp-8

Emilia Romagna: Emil-A1, Emil-A2, Emil-C1, Emil-C2, Emil-E1, Emil-E2, Emil-G1, Emil-G2, Emil-H1

Lazio: Lazi-C, Lazi-E, Lazi-G

Marche: Marc-1, Marc-2, Marc-3, Marc-4

Umbria: Umbr-A, Umbr-B, Umbr-C, Umbr-D, Umbr-E, Umbr-F

Per conoscere le zone di allerta di proprio interesse consultare il [link](#)



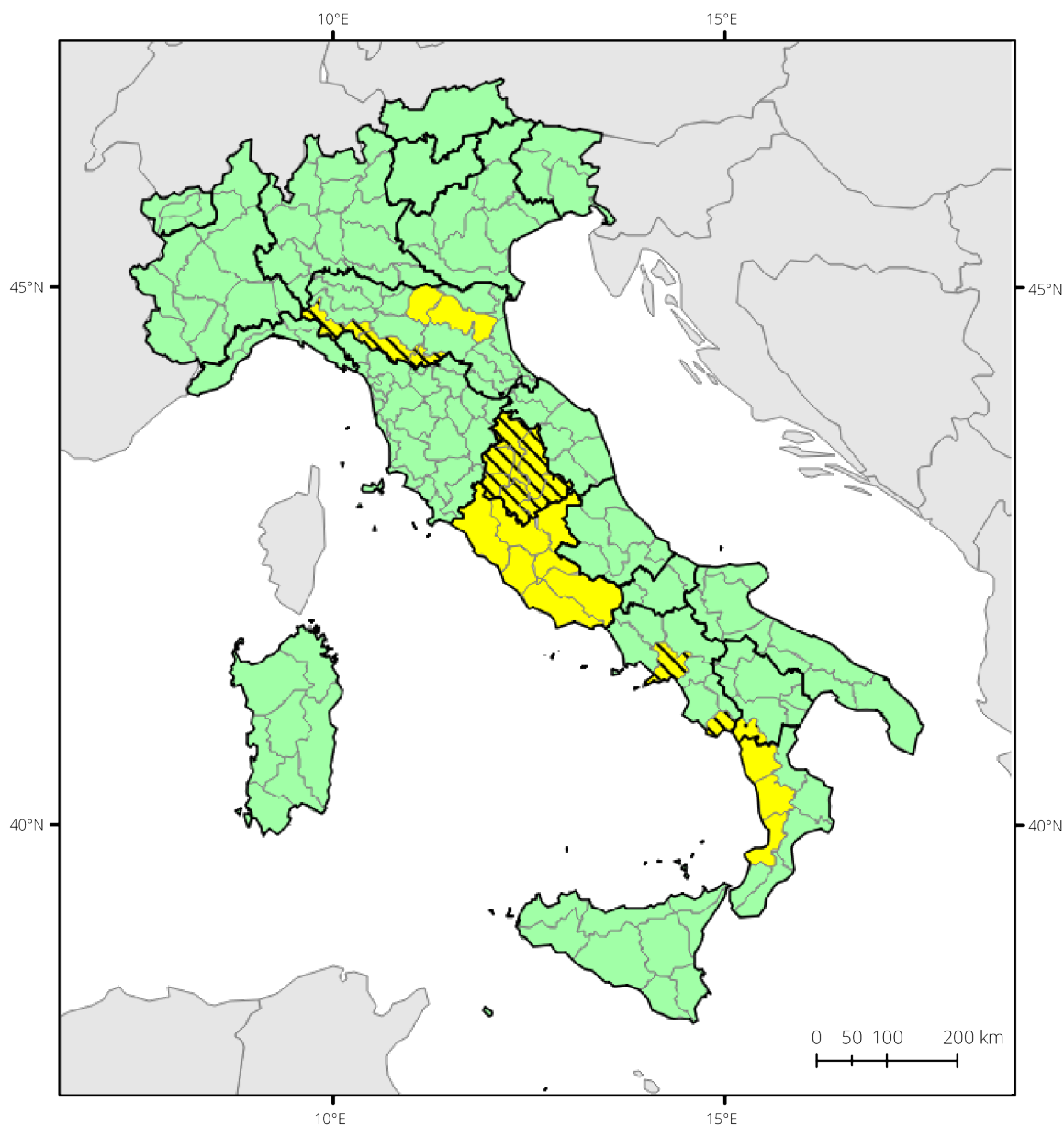
PROTEZIONE CIVILE
Presidenza del Consiglio dei Ministri
Dipartimento della Protezione Civile

Bollettino di criticità n° 042/2026
Giorno di emissione: venerdì 6 febbraio 2026

BOLLETTINO DI CRITICITA' NAZIONALE - ALLERTA DEL 06/02/2026

Effetti al suolo previsti per la giornata di domani, sabato 7 febbraio 2026

DOMANI



LEGENDA DI CRITICITÀ

RISCHIO IDRAULICO

- ELEVATA CRITICITÀ
ALLERTA ROSSA
- MODERATA CRITICITÀ
ALLERTA ARANCIONE
- ORDINARIA CRITICITÀ
ALLERTA GIALLA

RISCHIO TEMPORALI

- MODERATA CRITICITÀ
ALLERTA ARANCIONE
- ORDINARIA CRITICITÀ
ALLERTA GIALLA

RISCHIO IDROGEOLOGICO

- ELEVATA CRITICITÀ
ALLERTA ROSSA
- MODERATA CRITICITÀ
ALLERTA ARANCIONE
- ORDINARIA CRITICITÀ
ALLERTA GIALLA

ASSENZA DI FENOMENI
NESSUNA ALLERTA

VALUTAZIONE NON
TRASMESSA

Regioni
Zone di allerta

Ufficio II - Attività Tecnico Scientifiche per la Previsione e Prevenzione dei Rischi



PROTEZIONE CIVILE
Presidenza del Consiglio dei Ministri
Dipartimento della Protezione Civile

Bollettino di criticità n° 042/2026
Giorno di emissione: venerdì 6 febbraio 2026

BOLLETTINO DI CRITICITA' NAZIONALE - ALLERTA DEL 06/02/2026

Effetti al suolo previsti per la giornata di domani, sabato 7 febbraio 2026



RISCHIO IDRAULICO

- ELEVATA CRITICITÀ ALLERTA ROSSA
 - MODERATA CRITICITÀ ALLERTA ARANCIONE
 - ORDINARIA CRITICITÀ ALLERTA GIALLA
 - ASSENZA DI FENOMENI NESSUNA ALLERTA
 - VALUTAZIONE NON TRASMESSA
- Regioni
— Zone di allerta

NOTE:

nessuna



RISCHIO TEMPORALI

- MODERATA CRITICITÀ ALLERTA ARANCIONE
 - ORDINARIA CRITICITÀ ALLERTA GIALLA
 - ASSENZA DI FENOMENI NESSUNA ALLERTA
 - VALUTAZIONE NON TRASMESSA
- Regioni
— Zone di allerta



RISCHIO IDROGEOLOGICO

- ELEVATA CRITICITÀ ALLERTA ROSSA
 - MODERATA CRITICITÀ ALLERTA ARANCIONE
 - ORDINARIA CRITICITÀ ALLERTA GIALLA
 - ASSENZA DI FENOMENI NESSUNA ALLERTA
 - VALUTAZIONE NON TRASMESSA
- Regioni
— Zone di allerta

BOLLETTINO DI CRITICITA' NAZIONALE - ALLERTA DEL 06/02/2026

Effetti al suolo previsti per la giornata di domani, sabato 7 febbraio 2026

ELEVATA CRITICITÀ / ALLERTA ROSSA

PER RISCHIO IDRAULICO

Nessuna criticità

PER RISCHIO IDROGEOLOGICO

Nessuna criticità



MODERATA CRITICITÀ / ALLERTA ARANCIONE

PER RISCHIO IDRAULICO

Nessuna criticità

PER RISCHIO TEMPORALI

Nessuna criticità

PER RISCHIO IDROGEOLOGICO

Nessuna criticità



ORDINARIA CRITICITÀ / ALLERTA GIALLA

PER RISCHIO IDRAULICO

Calabria: Cala-1, Cala-2, Cala-3

Emilia Romagna: Emil-D1, Emil-F1

Lazio: Lazi-A, Lazi-B, Lazi-C, Lazi-D, Lazi-E, Lazi-F, Lazi-G

PER RISCHIO TEMPORALI

Basilicata: Basi-D

Calabria: Cala-1, Cala-2, Cala-3


PER RISCHIO IDROGEOLOGICO

Calabria: Cala-1, Cala-2, Cala-3

Campania: Camp-3, Camp-8

Emilia Romagna: Emil-C1, Emil-E1, Emil-G1

Lazio: Lazi-A, Lazi-B, Lazi-C, Lazi-D, Lazi-E, Lazi-F, Lazi-G





PROTEZIONE CIVILE
Presidenza del Consiglio dei Ministri
Dipartimento della Protezione Civile

Bollettino di criticità n° 042/2026
Giorno di emissione: **venerdì 6 febbraio 2026**

Umbria: Umbr-A, Umbr-B, Umbr-C, Umbr-D, Umbr-E, Umbr-F

Per conoscere le zone di allerta di proprio interesse consultare il **link**

BOLLETTINO DI CRITICITA' NAZIONALE - ALLERTA DEL 06/02/2026

Elementi informativi

Per completezza e per la corretta lettura del Bollettino di criticità nazionale, si tenga conto di quanto segue:

- È stato emesso in data odierna il Bollettino di Vigilanza meteorologica nazionale, visualizzabile al seguente [link](#);
- È in corso l'Avviso nazionale di condizioni meteorologiche avverse n° 26013 prot. n° 5982 datato 05.02.2026;
- È stato emesso l'avviso di criticità della Regione Lazio.

Il Centro Funzionale Centrale emette il Bollettino di criticità nazionale in attuazione delle seguenti disposizioni:

- Decreto legislativo 2 gennaio 2018, n. 1, "Codice della protezione civile", in particolare l'articolo 2, comma 2 e comma 4, lettera a) e l'articolo 17;
- Direttiva del Presidente del Consiglio dei ministri del 27 febbraio 2004, pubblicata nella Gazzetta Ufficiale n. 59 del 11 marzo 2004 "Indirizzi operativi per la gestione organizzativa e funzionale del sistema di allertamento nazionale e regionale per il rischio idrogeologico ed idraulico ai fini di protezione civile";
- Direttiva del Presidente del Consiglio dei Ministri del 25 febbraio 2005, pubblicata nella Gazzetta Ufficiale n. 55 del 8 marzo 2005, "Ulteriori Indirizzi operativi per la gestione organizzativa e funzionale del sistema di allertamento nazionale, statale e regionale, per il rischio idrogeologico e idraulico ai fini di protezione civile, recanti modifiche ed integrazioni alla Direttiva del Presidente del Consiglio dei Ministri del 27 febbraio 2004";
- Indicazioni operative recanti "Metodi e criteri per l'omogeneizzazione dei messaggi del Sistema di allertamento nazionale per il rischio meteo-idrologico e idraulico e della risposta del sistema di protezione civile", impartite dal Capo Dipartimento della protezione civile, con nota prot. n. RIA/0007117 del 10 febbraio 2016.

Il Bollettino di criticità nazionale è emesso dal Centro Funzionale Centrale a seguito del recepimento delle criticità previste dai Centri Funzionali Decentrati delle Regioni o Province autonome competenti in materia nel proprio territorio. Le criticità vengono comunicate dai soggetti suddetti al Centro Funzionale Centrale utilizzando una Piattaforma informatica, ai cui "Termini e Condizioni" e "Disclaimer" si rimanda integralmente per quanto concerne l'utilizzo della Piattaforma stessa.

Il Bollettino di criticità nazionale è pubblicato dal Centro Funzionale Centrale di norma entro le ore 16,00 ora locale di ogni giorno, e contiene le previsioni di criticità e i livelli di allerta emessi dalle Regioni o Province autonome per il giorno corrente (di norma, dalle 16,00 alle 24,00) e per il giorno seguente (dalle 00,00 alle 24,00), per le zone d'allerta di loro competenza.

Le previsioni di criticità e i livelli di allerta contenuti nel Bollettino di criticità nazionale sono strumenti finalizzati al preannuncio in termini probabilistici, sulla base delle conoscenze disponibili, degli eventi e della conseguente evoluzione degli scenari di rischio al fine di attivare il Servizio nazionale della protezione civile ai diversi livelli territoriali.

Venerdì 6 febbraio 2026

Il Dirigente