

BOLLETTINO DI CRITICITA' NAZIONALE - ALLERTA DEL 01/06/2026


Il **Centro Funzionale Centrale**, recepite le criticità comunicate dai Centri Funzionali Decentrati di tutte le Regioni e Province Autonome, **emette il bollettino di criticità nazionale / allerta**.

OGGI

Allerta meteo-idro gialla per oggi, lunedì 1 giugno 2026

Consulta il bollettino per conoscere il livello e le zone di allerta sul tuo territorio

ALLERTA GIALLA METEO-IDRO




- ALLERTA ROSSA
- ALLERTA ARANCIONE
- **ALLERTA GIALLA**
- NESSUNA ALLERTA

DOMANI

Allerta meteo-idro gialla per domani, martedì 2 giugno 2026

Consulta il bollettino per conoscere il livello e le zone di allerta sul tuo territorio

ALLERTA GIALLA METEO-IDRO



- ALLERTA ROSSA
- ALLERTA ARANCIONE
- **ALLERTA GIALLA**
- NESSUNA ALLERTA



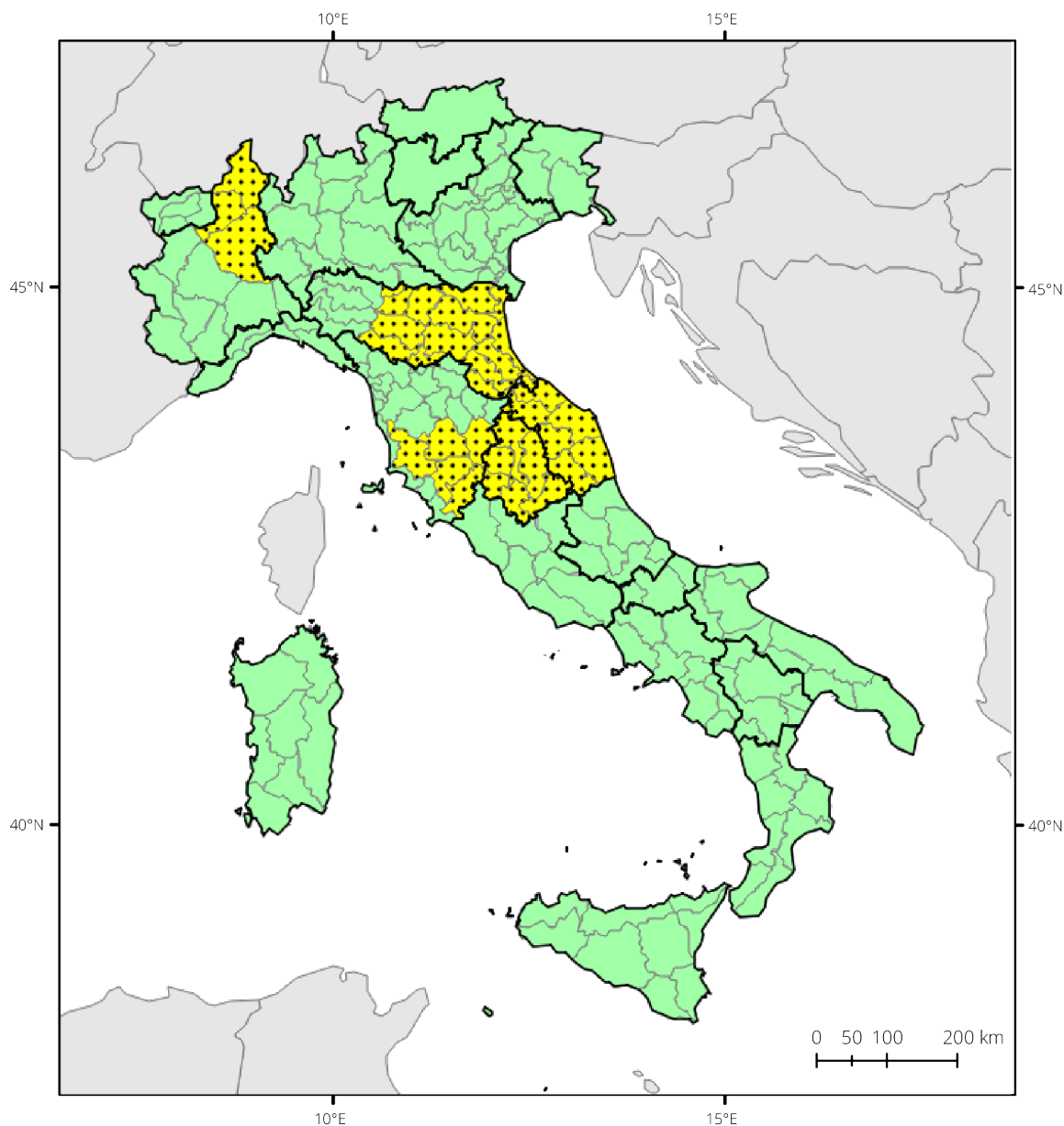
PROTEZIONE CIVILE
Presidenza del Consiglio dei Ministri
Dipartimento della Protezione Civile

Bollettino di criticità n° 168/2026
Giorno di emissione: lunedì 1 giugno 2026

BOLLETTINO DI CRITICITA' NAZIONALE - ALLERTA DEL 01/06/2026

Effetti al suolo previsti per la giornata di oggi, lunedì 1 giugno 2026

OGGI



| LEGENDA DI CRITICITÀ | | |
|---|---|---|
| RISCHIO IDRAULICO | RISCHIO TEMPORALI | RISCHIO IDROGEOLOGICO |
| ELEVATA CRITICITÀ ALLERTA ROSSA | MODERATA CRITICITÀ ALLERTA ARANCIONE | ELEVATA CRITICITÀ ALLERTA ROSSA |
| MODERATA CRITICITÀ ALLERTA ARANCIONE | ORDINARIA CRITICITÀ ALLERTA GIALLA | MODERATA CRITICITÀ ALLERTA ARANCIONE |
| ORDINARIA CRITICITÀ ALLERTA GIALLA | | ORDINARIA CRITICITÀ ALLERTA GIALLA |
| ASSENZA DI FENOMENI NESSUNA ALLERTA | VALUTAZIONE NON TRASMESSA | Regioni |
| | | Zone di allerta |

Ufficio II - Attività Tecnico Scientifiche per la Previsione e Prevenzione dei Rischi

BOLLETTINO DI CRITICITA' NAZIONALE - ALLERTA DEL 01/06/2026

Effetti al suolo previsti per la giornata di oggi, lunedì 1 giugno 2026

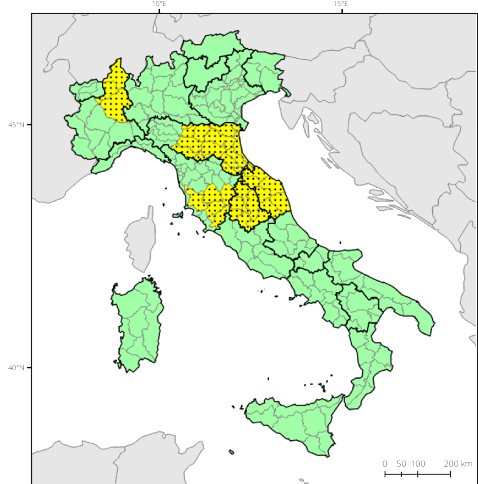


RISCHIO IDRAULICO

- ELEVATA CRITICITÀ
ALLERTA ROSSA
- MODERATA CRITICITÀ
ALLERTA ARANCIONE
- ORDINARIA CRITICITÀ
ALLERTA GIALLA
- ASSENZA DI FENOMENI
NESSUNA ALLERTA
- VALUTAZIONE NON TRASMESSA
- Regioni
- Zone di allerta

NOTE:

Regione Toscana: per la validità temporale delle criticità si rimanda al bollettino regionale.



RISCHIO TEMPORALI

- MODERATA CRITICITÀ
ALLERTA ARANCIONE
- ORDINARIA CRITICITÀ
ALLERTA GIALLA
- ASSENZA DI FENOMENI
NESSUNA ALLERTA
- VALUTAZIONE NON TRASMESSA
- Regioni
- Zone di allerta



RISCHIO IDROGEOLOGICO

- ELEVATA CRITICITÀ
ALLERTA ROSSA
- MODERATA CRITICITÀ
ALLERTA ARANCIONE
- ORDINARIA CRITICITÀ
ALLERTA GIALLA
- ASSENZA DI FENOMENI
NESSUNA ALLERTA
- VALUTAZIONE NON TRASMESSA
- Regioni
- Zone di allerta

BOLLETTINO DI CRITICITA' NAZIONALE - ALLERTA DEL 01/06/2026

Effetti al suolo previsti per la giornata di oggi, lunedì 1 giugno 2026

ELEVATA CRITICITÀ / ALLERTA ROSSA

PER RISCHIO IDRAULICO

Nessuna criticità

PER RISCHIO IDROGEOLOGICO

Nessuna criticità



MODERATA CRITICITÀ / ALLERTA ARANCIONE

PER RISCHIO IDRAULICO

Nessuna criticità

PER RISCHIO TEMPORALI

Nessuna criticità

PER RISCHIO IDROGEOLOGICO

Nessuna criticità



ORDINARIA CRITICITÀ / ALLERTA GIALLA

PER RISCHIO IDRAULICO

Nessuna criticità

PER RISCHIO TEMPORALI

Emilia Romagna: Emil-A1, Emil-A2, Emil-B1, Emil-B2, Emil-C1, Emil-C2, Emil-D1, Emil-D2, Emil-D3, Emil-E1, Emil-E2, Emil-F1, Emil-F2, Emil-F3

Marche: Marc-1, Marc-2, Marc-3, Marc-4, Marc-5, Marc-6


Piemonte: Piem-A, Piem-B, Piem-I

Toscana: Tosc-C, Tosc-E1, Tosc-F1, Tosc-O1, Tosc-O2

Umbria: Umbr-A, Umbr-B, Umbr-C, Umbr-D, Umbr-E, Umbr-F

PER RISCHIO IDROGEOLOGICO

Nessuna criticità





PROTEZIONE CIVILE
Presidenza del Consiglio dei Ministri
Dipartimento della Protezione Civile

Bollettino di criticità n° 168/2026
Giorno di emissione: **lunedì 1 giugno 2026**

Per conoscere le zone di allerta di proprio interesse consultare il **[link](#)**



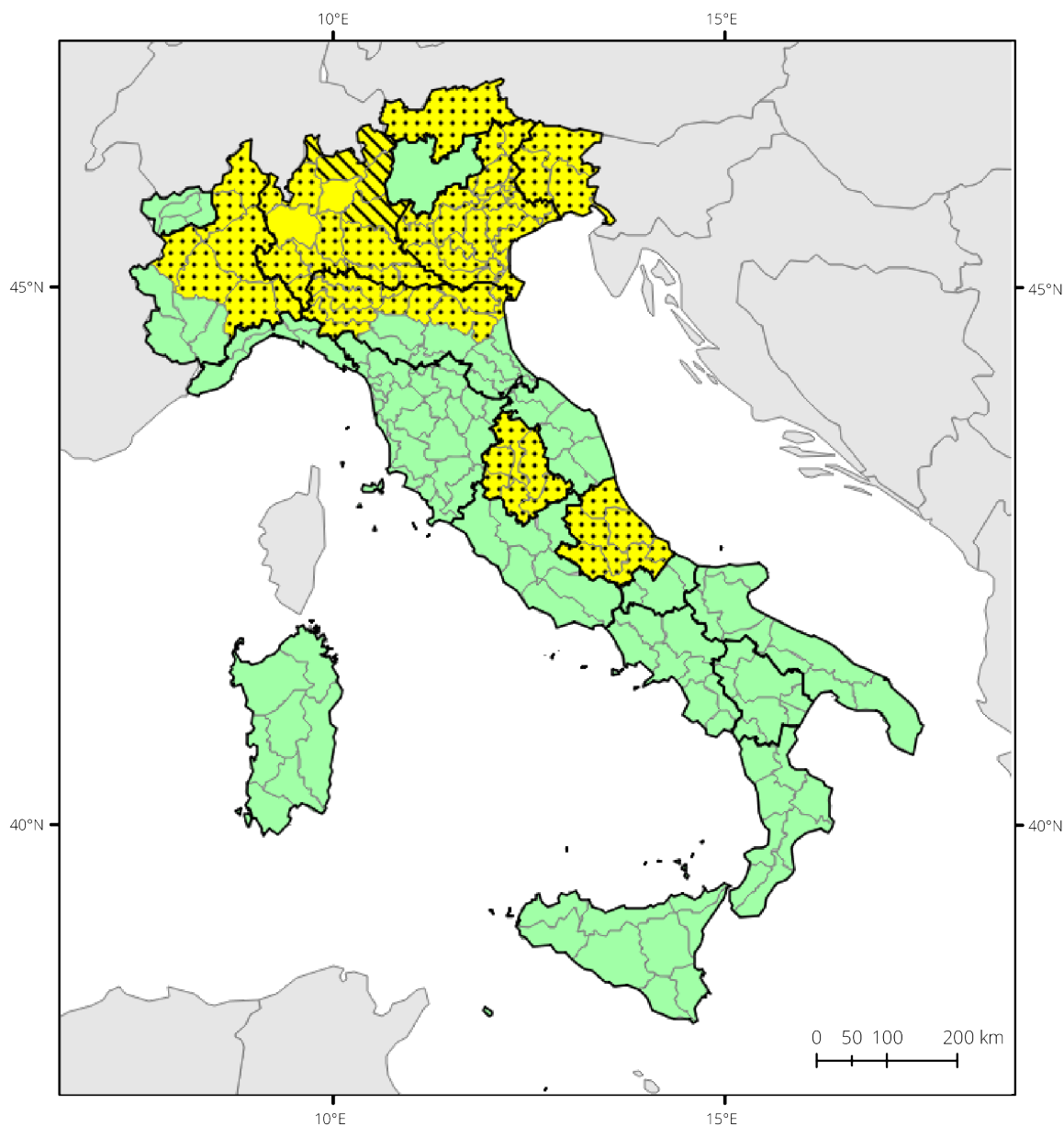
PROTEZIONE CIVILE
Presidenza del Consiglio dei Ministri
Dipartimento della Protezione Civile

Bollettino di criticità n° 168/2026
Giorno di emissione: lunedì 1 giugno 2026

BOLLETTINO DI CRITICITA' NAZIONALE - ALLERTA DEL 01/06/2026

Effetti al suolo previsti per la giornata di domani, martedì 2 giugno 2026

DOMANI

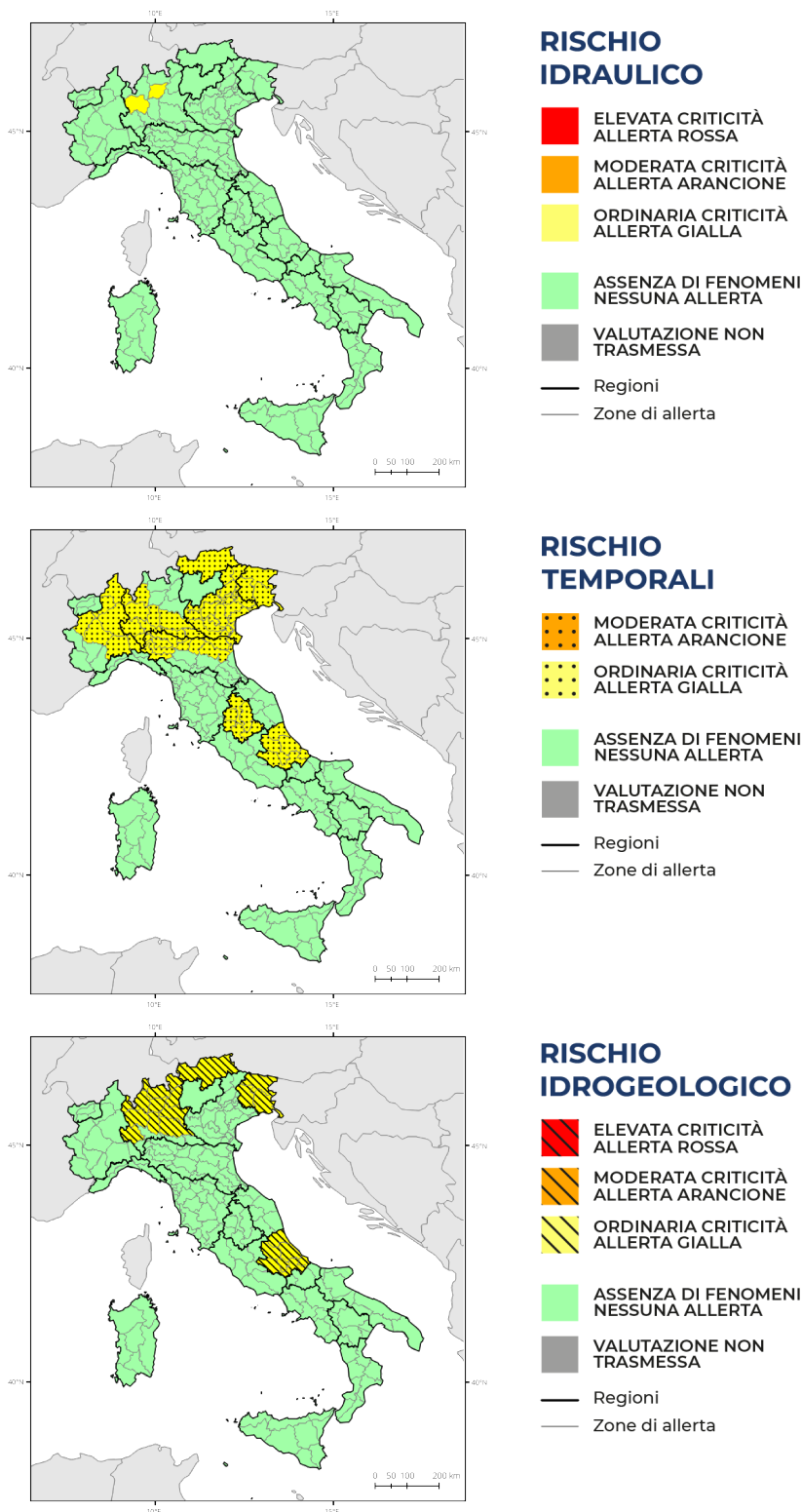


| LEGENDA DI CRITICITÀ | | |
|---|---|---|
| RISCHIO IDRAULICO | RISCHIO TEMPORALI | RISCHIO IDROGEOLOGICO |
| ELEVATA CRITICITÀ ALLERTA ROSSA | MODERATA CRITICITÀ ALLERTA ARANCIONE | ELEVATA CRITICITÀ ALLERTA ROSSA |
| MODERATA CRITICITÀ ALLERTA ARANCIONE | ORDINARIA CRITICITÀ ALLERTA GIALLA | MODERATA CRITICITÀ ALLERTA ARANCIONE |
| ORDINARIA CRITICITÀ ALLERTA GIALLA | | ORDINARIA CRITICITÀ ALLERTA GIALLA |
| ASSENZA DI FENOMENI NESSUNA ALLERTA | VALUTAZIONE NON TRASMESSA | Regioni |
| | | Zone di allerta |

Ufficio II - Attività Tecnico Scientifiche per la Previsione e Prevenzione dei Rischi

BOLLETTINO DI CRITICITA' NAZIONALE - ALLERTA DEL 01/06/2026

Effetti al suolo previsti per la giornata di domani, martedì 2 giugno 2026



NOTE:

Regioni Lombardia e Friuli Venezia Giulia:
per la validità temporale delle criticità si
rimanda ai rispettivi bollettini regionali.

BOLLETTINO DI CRITICITA' NAZIONALE - ALLERTA DEL 01/06/2026

Effetti al suolo previsti per la giornata di domani, martedì 2 giugno 2026

ELEVATA CRITICITÀ / ALLERTA ROSSA

PER RISCHIO IDRAULICO

Nessuna criticità

PER RISCHIO IDROGEOLOGICO

Nessuna criticità



MODERATA CRITICITÀ / ALLERTA ARANCIONE

PER RISCHIO IDRAULICO

Nessuna criticità

PER RISCHIO TEMPORALI

Nessuna criticità

PER RISCHIO IDROGEOLOGICO

Nessuna criticità



ORDINARIA CRITICITÀ / ALLERTA GIALLA

PER RISCHIO IDRAULICO

Lombardia: Lomb-06, Lomb-09

PER RISCHIO TEMPORALI

Abruzzo: Abru-A, Abru-B, Abru-C, Abru-D1, Abru-D2, Abru-E

Emilia Romagna: Emil-D1, Emil-D2, Emil-D3, Emil-F1, Emil-F2, Emil-F3, Emil-G1, Emil-G2, Emil-H1, Emil-H2

Friuli Venezia Giulia: Friu-A, Friu-B, Friu-C, Friu-D


Lombardia: Lomb-04, Lomb-05, Lomb-09, Lomb-10, Lomb-11, Lomb-12, Lomb-13, Lomb-14, Lomb-15, Lomb-16

Piemonte: Piem-A, Piem-B, Piem-C, Piem-G, Piem-H, Piem-I, Piem-L

Trentino Alto Adige: Tren-A

Umbria: Umbr-A, Umbr-B, Umbr-C, Umbr-D, Umbr-E, Umbr-F

Veneto: Vene-A1, Vene-A2, Vene-B1, Vene-B2, Vene-B3, Vene-C1, Vene-C2, Vene-D1, Vene-D2, Vene-D3,





PROTEZIONE CIVILE
Presidenza del Consiglio dei Ministri
Dipartimento della Protezione Civile

Bollettino di criticità n° 168/2026
Giorno di emissione: **lunedì 1 giugno 2026**

Vene-E1, Vene-E2, Vene-E3, Vene-E4, Vene-E5, Vene-F1, Vene-F2, Vene-G1, Vene-G2, Vene-H1, Vene-H2,
Vene-H3, Vene-H4, Vene-H5, Vene-H6

PER RISCHIO IDROGEOLOGICO

Abruzzo: Abru-A, Abru-B, Abru-C, Abru-D1, Abru-D2, Abru-E

Friuli Venezia Giulia: Friu-A, Friu-B, Friu-C, Friu-D

Lombardia: Lomb-01, Lomb-02, Lomb-03, Lomb-04, Lomb-05, Lomb-06, Lomb-07, Lomb-08,
Lomb-09, Lomb-10, Lomb-11, Lomb-12

Trentino Alto Adige: Tren-A

Per conoscere le zone di allerta di proprio interesse consultare il **link**

BOLLETTINO DI CRITICITA' NAZIONALE - ALLERTA DEL 01/06/2026

Elementi informativi

Per completezza e per la corretta lettura del Bollettino di criticità nazionale, si tenga conto di quanto segue:

- È stato emesso in data odierna il Bollettino di Vigilanza meteorologica nazionale, visualizzabile al seguente [link](#);
- È stato emesso l'Avviso nazionale di condizioni meteorologiche avverse n. 26042 prot. n. 25391 datato 01.06.2026;
- Non è stato emesso e non è in corso alcun Avviso di criticità.

Il Centro Funzionale Centrale emette il Bollettino di criticità nazionale in attuazione delle seguenti disposizioni:

- Decreto legislativo 2 gennaio 2018, n. 1, "Codice della protezione civile", in particolare l'articolo 2, comma 2 e comma 4, lettera a) e l'articolo 17;
- Direttiva del Presidente del Consiglio dei ministri del 27 febbraio 2004, pubblicata nella Gazzetta Ufficiale n. 59 del 11 marzo 2004 "Indirizzi operativi per la gestione organizzativa e funzionale del sistema di allertamento nazionale e regionale per il rischio idrogeologico ed idraulico ai fini di protezione civile";
- Direttiva del Presidente del Consiglio dei Ministri del 25 febbraio 2005, pubblicata nella Gazzetta Ufficiale n. 55 del 8 marzo 2005, "Ulteriori Indirizzi operativi per la gestione organizzativa e funzionale del sistema di allertamento nazionale, statale e regionale, per il rischio idrogeologico e idraulico ai fini di protezione civile, recanti modifiche ed integrazioni alla Direttiva del Presidente del Consiglio dei Ministri del 27 febbraio 2004";
- Indicazioni operative recanti "Metodi e criteri per l'omogeneizzazione dei messaggi del Sistema di allertamento nazionale per il rischio meteo-idrologico e idraulico e della risposta del sistema di protezione civile", impartite dal Capo Dipartimento della protezione civile, con nota prot. n. RIA/0007117 del 10 febbraio 2016.

Il Bollettino di criticità nazionale è emesso dal Centro Funzionale Centrale a seguito del recepimento delle criticità previste dai Centri Funzionali Decentrati delle Regioni o Province autonome competenti in materia nel proprio territorio. Le criticità vengono comunicate dai soggetti suddetti al Centro Funzionale Centrale utilizzando una Piattaforma informatica, ai cui "Termini e Condizioni" e "Disclaimer" si rimanda integralmente per quanto concerne l'utilizzo della Piattaforma stessa.

Il Bollettino di criticità nazionale è pubblicato dal Centro Funzionale Centrale di norma entro le ore 16,00 ora locale di ogni giorno, e contiene le previsioni di criticità e i livelli di allerta emessi dalle Regioni o Province autonome per il giorno corrente (di norma, dalle 16,00 alle 24,00) e per il giorno seguente (dalle 00,00 alle 24,00), per le zone d'allerta di loro competenza.

Le previsioni di criticità e i livelli di allerta contenuti nel Bollettino di criticità nazionale sono strumenti finalizzati al preannuncio in termini probabilistici, sulla base delle conoscenze disponibili, degli eventi e della conseguente evoluzione degli scenari di rischio al fine di attivare il Servizio nazionale della protezione civile ai diversi livelli territoriali.

Lunedì 1 giugno 2026

Il Dirigente