BOLLETTINO DI CRITICITA' NAZIONALE - ALLERTA DEL 24/11/2026

Il Centro Funzionale Centrale, recepite le criticità comunicate dai Centri Funzionali Decentrati di tutte le Regioni e Province Autonome, **emette il bollettino di criticità nazionale / allerta.**

OGGI

Nessuna allerta meteo-idro per oggi, martedì 24 novembre 2026

Consulta il bollettino per conoscere il livello e le zone di allerta sul tuo territorio



DOMANI

Allerta meteo-idro arancione per domani, mercoledì 25 novembre 2026

Consulta il bollettino per conoscere il livello e le zone di allerta sul tuo territorio



Ufficio II – Previsione e prevenzione del rischio

BOLLETTINO DI CRITICITA' NAZIONALE - ALLERTA DEL 24/11/2026
Effetti al suolo previsti per la giornata di oggi, martedì 24 novembre 2026

OGGI

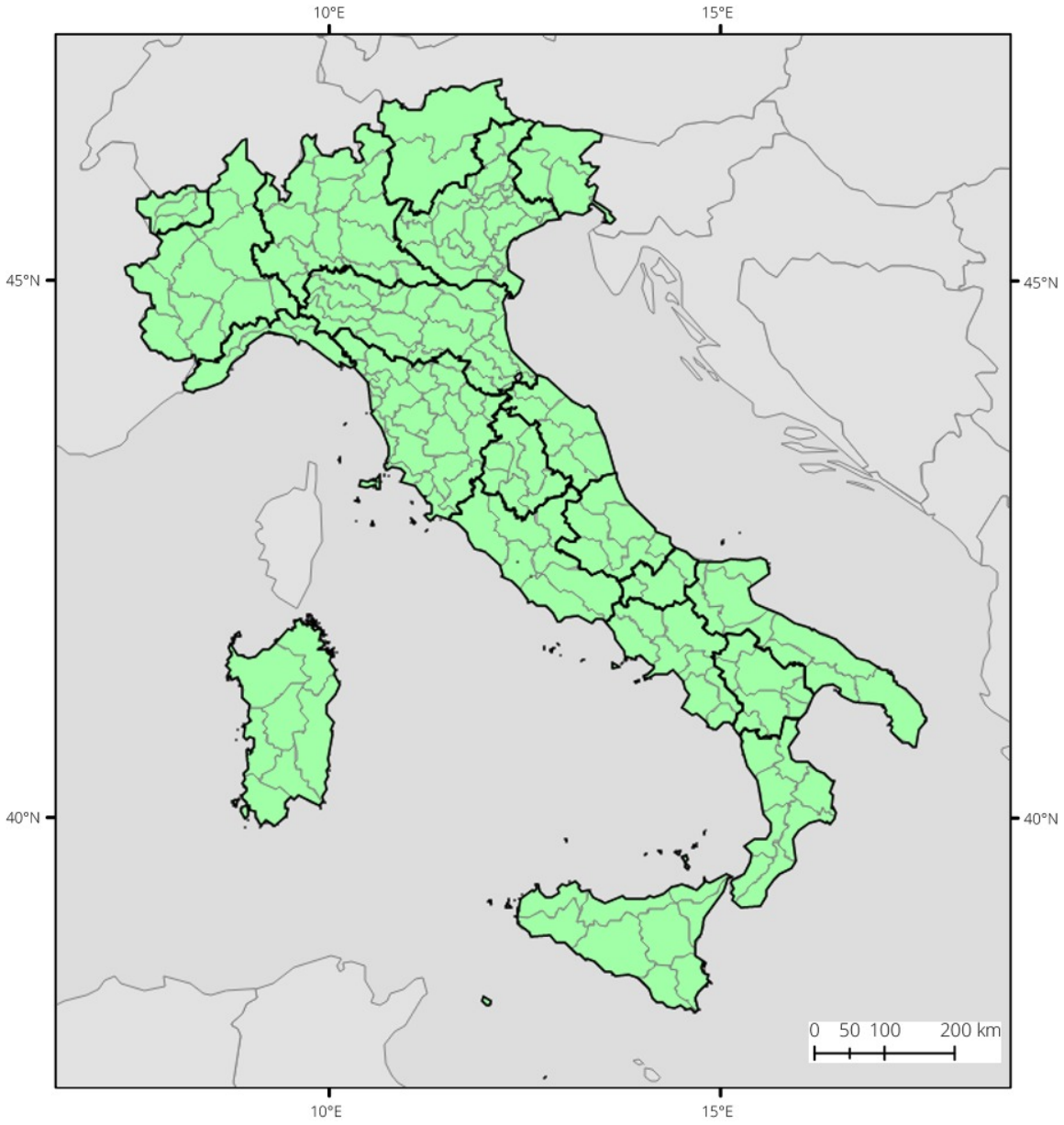

LEGENDA DI CRITICITÀ

RISCHIO IDRAULICO
- ELEVATA CRITICITÀ ALLERTA ROSSA
- MODERATA CRITICITÀ ALLERTA ARANCIONE
- ORDINARIA CRITICITÀ ALLERTA GIALLA

RISCHIO TEMPORALI
- MODERATA CRITICITÀ ALLERTA ARANCIONE
- ORDINARIA CRITICITÀ ALLERTA GIALLA

RISCHIO IDROGEOLOGICO
- ELEVATA CRITICITÀ ALLERTA ROSSA
- MODERATA CRITICITÀ ALLERTA ARANCIONE
- ORDINARIA CRITICITÀ ALLERTA GIALLA

- ASSENZA DI FENOMENI NESSUNA ALLERTA
- VALUTAZIONE NON TRASMESSA
- Regioni
- Zone di allerta

BOLLETTINO DI CRITICITA' NAZIONALE - ALLERTA DEL 24/11/2026
Effetti al suolo previsti per la giornata di oggi, martedì 24 novembre 2026

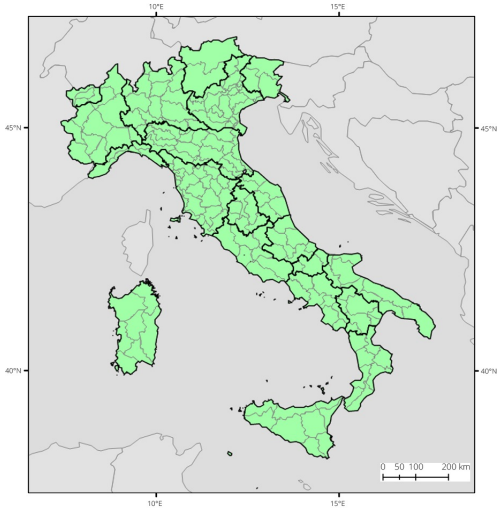

RISCHIO IDRAULICO

- ELEVATA CRITICITÀ ALLERTA ROSSA
- MODERATA CRITICITÀ ALLERTA ARANCIONE
- ORDINARIA CRITICITÀ ALLERTA GIALLA
- ASSENZA DI FENOMENI NESSUNA ALLERTA
- VALUTAZIONE NON TRASMESSA
- Regioni
- Zone di allerta

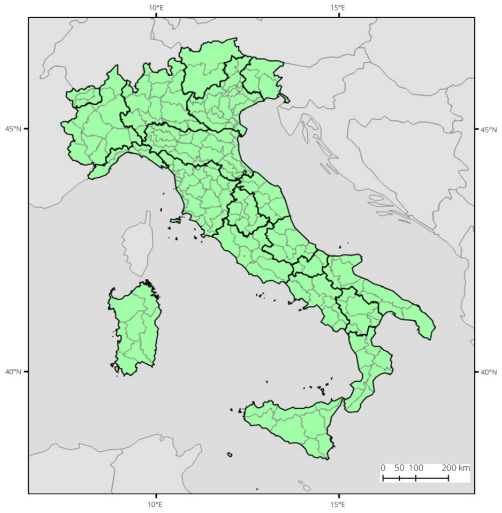

RISCHIO TEMPORALI

- MODERATA CRITICITÀ ALLERTA ARANCIONE
- ORDINARIA CRITICITÀ ALLERTA GIALLA
- ASSENZA DI FENOMENI NESSUNA ALLERTA
- VALUTAZIONE NON TRASMESSA
- Regioni
- Zone di allerta

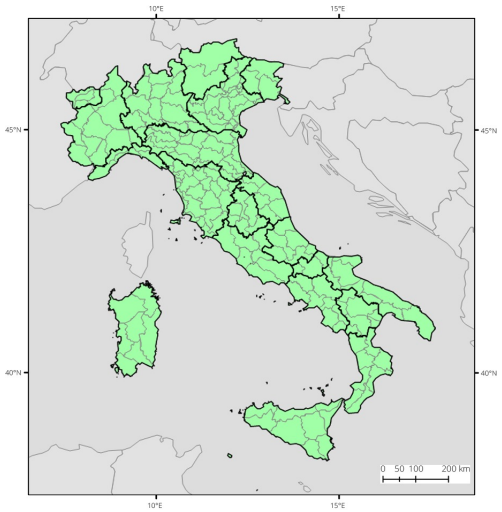

RISCHIO IDROGEOLOGICO

- ELEVATA CRITICITÀ ALLERTA ROSSA
- MODERATA CRITICITÀ ALLERTA ARANCIONE
- ORDINARIA CRITICITÀ ALLERTA GIALLA
- ASSENZA DI FENOMENI NESSUNA ALLERTA
- VALUTAZIONE NON TRASMESSA
- Regioni
- Zone di allerta

NOTE:
nessuna

BOLLETTINO DI CRITICITA' NAZIONALE - ALLERTA DEL 24/11/2026
Effetti al suolo previsti per la giornata di oggi, martedì 24 novembre 2026

ELEVATA CRITICITÀ / ALLERTA ROSSA



PER RISCHIO IDRAULICO
Nessuna criticità

PER RISCHIO IDROGEOLOGICO
Nessuna criticità

MODERATA CRITICITÀ / ALLERTA ARANCIONE



PER RISCHIO IDRAULICO
Nessuna criticità

PER RISCHIO TEMPORALI
Nessuna criticità

PER RISCHIO IDROGEOLOGICO
Nessuna criticità

ORDINARIA CRITICITÀ / ALLERTA GIALLA



PER RISCHIO IDRAULICO
Nessuna criticità

PER RISCHIO TEMPORALI
Nessuna criticità

PER RISCHIO IDROGEOLOGICO
Nessuna criticità

Per conoscere le zone di allerta di proprio interesse consultare il **link**

BOLLETTINO DI CRITICITA' NAZIONALE - ALLERTA DEL 24/11/2026
Effetti al suolo previsti per la giornata di domani, mercoledì 25 novembre 2026

DOMANI

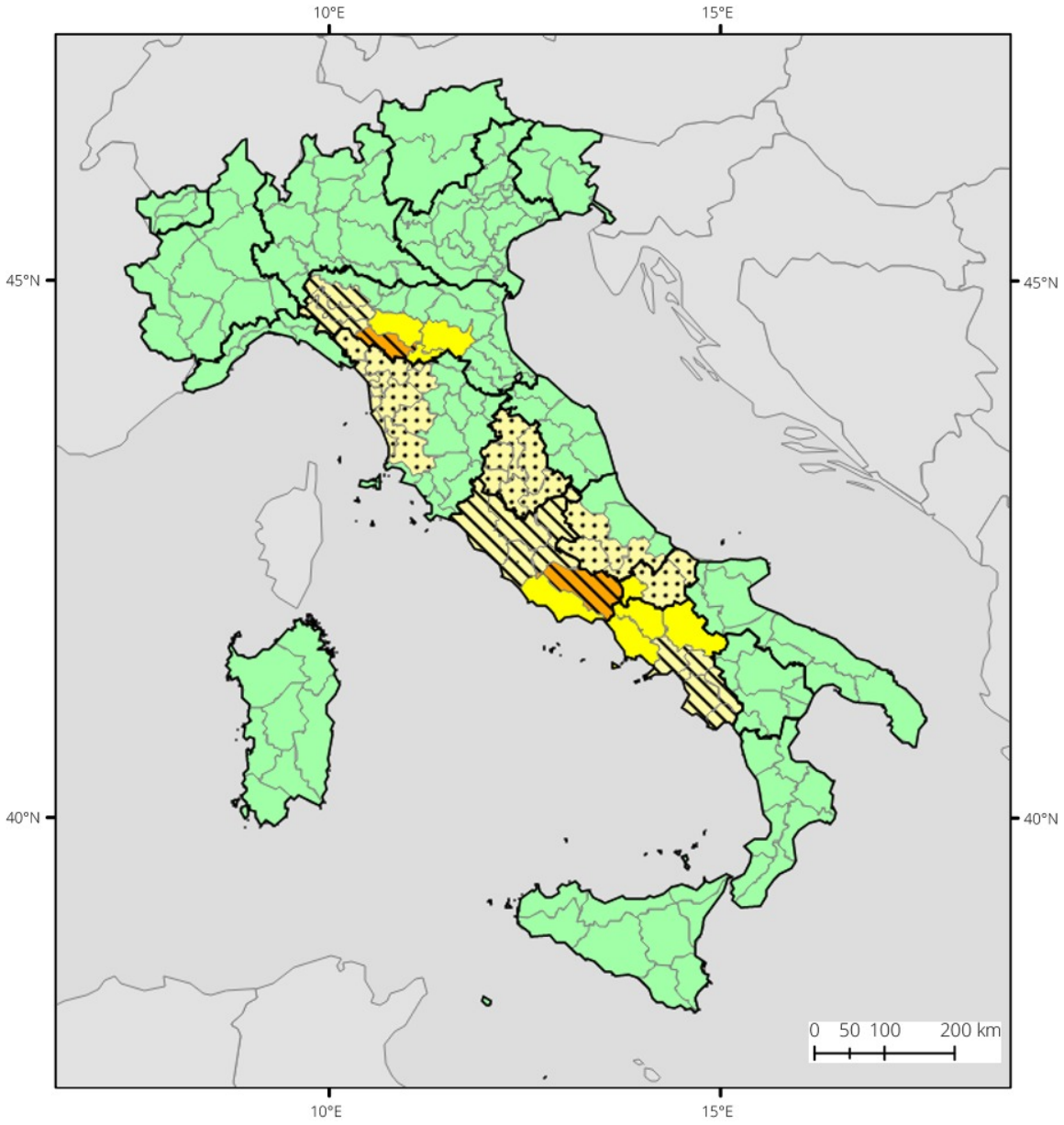

LEGENDA DI CRITICITÀ

RISCHIO IDRAULICO
- ELEVATA CRITICITÀ ALLERTA ROSSA
- MODERATA CRITICITÀ ALLERTA ARANCIONE
- ORDINARIA CRITICITÀ ALLERTA GIALLA

RISCHIO TEMPORALI
- MODERATA CRITICITÀ ALLERTA ARANCIONE
- ORDINARIA CRITICITÀ ALLERTA GIALLA

RISCHIO IDROGEOLOGICO
- ELEVATA CRITICITÀ ALLERTA ROSSA
- MODERATA CRITICITÀ ALLERTA ARANCIONE
- ORDINARIA CRITICITÀ ALLERTA GIALLA

- ASSENZA DI FENOMENI NESSUNA ALLERTA
- VALUTAZIONE NON TRASMESSA
- Regioni
- Zone di allerta

BOLLETTINO DI CRITICITA' NAZIONALE - ALLERTA DEL 24/11/2026
Effetti al suolo previsti per la giornata di domani, mercoledì 25 novembre 2026

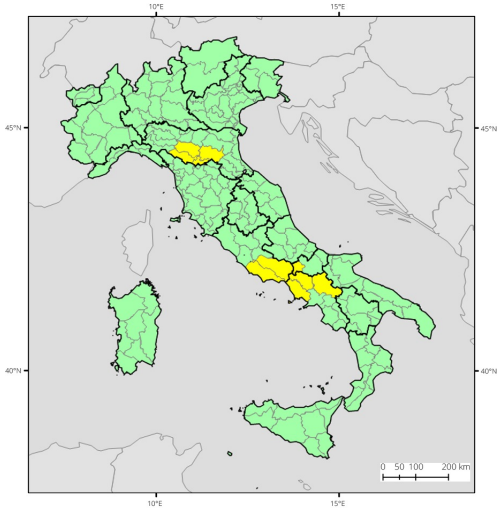

RISCHIO IDRAULICO

- ELEVATA CRITICITÀ ALLERTA ROSSA
- MODERATA CRITICITÀ ALLERTA ARANCIONE
- ORDINARIA CRITICITÀ ALLERTA GIALLA
- ASSENZA DI FENOMENI NESSUNA ALLERTA
- VALUTAZIONE NON TRASMESSA
- Regioni
- Zone di allerta

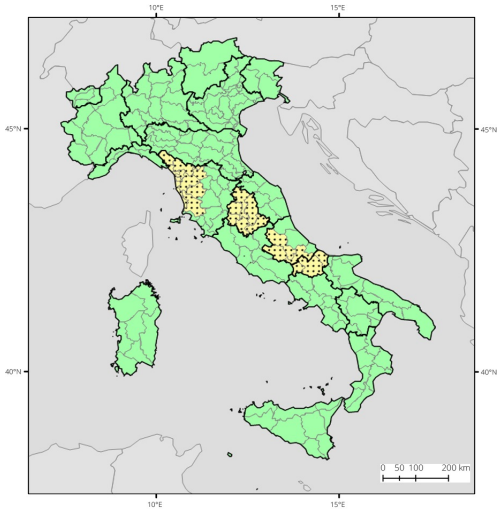

RISCHIO TEMPORALI

- MODERATA CRITICITÀ ALLERTA ARANCIONE
- ORDINARIA CRITICITÀ ALLERTA GIALLA
- ASSENZA DI FENOMENI NESSUNA ALLERTA
- VALUTAZIONE NON TRASMESSA
- Regioni
- Zone di allerta

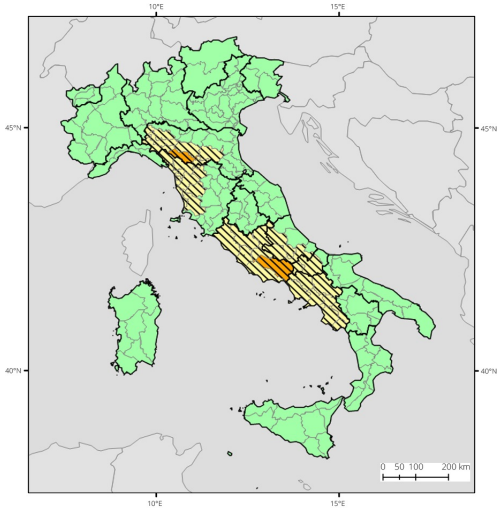

RISCHIO IDROGEOLOGICO

- ELEVATA CRITICITÀ ALLERTA ROSSA
- MODERATA CRITICITÀ ALLERTA ARANCIONE
- ORDINARIA CRITICITÀ ALLERTA GIALLA
- ASSENZA DI FENOMENI NESSUNA ALLERTA
- VALUTAZIONE NON TRASMESSA
- Regioni
- Zone di allerta

NOTE:
Regioni Toscana e Campania: per la validità temporale delle criticità si rimanda ai rispettivi bollettini regionali.

BOLLETTINO DI CRITICITA' NAZIONALE - ALLERTA DEL 24/11/2026
Effetti al suolo previsti per la giornata di domani, mercoledì 25 novembre 2026

ELEVATA CRITICITÀ / ALLERTA ROSSA



PER RISCHIO IDRAULICO
Nessuna criticità

PER RISCHIO IDROGEOLOGICO
Nessuna criticità

MODERATA CRITICITÀ / ALLERTA ARANCIONE



PER RISCHIO IDRAULICO
Nessuna criticità

PER RISCHIO TEMPORALI
Nessuna criticità

PER RISCHIO IDROGEOLOGICO
Emilia Romagna: Emil-E1
Lazio: Lazi-G

ORDINARIA CRITICITÀ / ALLERTA GIALLA



PER RISCHIO IDRAULICO
Campania: Camp-1, Camp-2, Camp-4
Emilia Romagna: Emil-C1, Emil-C2, Emil-E1, Emil-E2
Lazio: Lazi-F, Lazi-G
Molise: Moli-A

PER RISCHIO TEMPORALI
Abruzzo: Abru-B, Abru-D1, Abru-E
Molise: Moli-A, Moli-B, Moli-C
Toscana: Tosc-A4, Tosc-A5, Tosc-A6, Tosc-B, Tosc-E1, Tosc-E2, Tosc-L, Tosc-R1, Tosc-S1, Tosc-S2, Tosc-S3, Tosc-V
Umbria: Umbr-A, Umbr-B, Umbr-C, Umbr-D, Umbr-E, Umbr-F

PER RISCHIO IDROGEOLOGICO

Abruzzo: Abru-B, Abru-D1, Abru-E

Campania: Camp-1, Camp-2, Camp-3, Camp-4, Camp-5, Camp-6, Camp-7, Camp-8

Emilia Romagna: Emil-C1, Emil-C2, Emil-E2, Emil-G1, Emil-G2, Emil-H1

Lazio: Lazi-A, Lazi-B, Lazi-C, Lazi-D, Lazi-E, Lazi-F

Molise: Moli-A, Moli-B

Toscana: Tosc-A4, Tosc-A5, Tosc-A6, Tosc-B, Tosc-E1, Tosc-E2, Tosc-L, Tosc-R1, Tosc-S1, Tosc-S2, Tosc-S3, Tosc-V

Per conoscere le zone di allerta di proprio interesse consultare il **link**

BOLLETTINO DI CRITICITA' NAZIONALE - ALLERTA DEL 24/11/2026

Elementi informativi

Per completezza e per la corretta lettura del Bollettino di criticità nazionale, si tenga conto di quanto segue:

- È stato emesso in data odierna il Bollettino di Vigilanza meteorologica nazionale, visualizzabile al seguente **link**;
- È stato emesso l'Avviso nazionale di condizioni meteorologiche avverse nr. 26079 prot. nr. 54495 datato 24/11/2026;
- È stato emesso l'avviso di criticità per le Regioni Emilia Romagna e Lazio.

Il Centro Funzionale Centrale emette il Bollettino di criticità nazionale in attuazione delle seguenti disposizioni:

- Decreto legislativo 2 gennaio 2018, n. 1, "Codice della protezione civile", in particolare l'articolo 2, comma 2 e comma 4, lettera a) e l'articolo 17;
- Direttiva del Presidente del Consiglio dei ministri del 27 febbraio 2004, pubblicata nella Gazzetta Ufficiale n. 59 del 11 marzo 2004 "Indirizzi operativi per la gestione organizzativa e funzionale del sistema di allertamento nazionale e regionale per il rischio idrogeologico ed idraulico ai fini di protezione civile";
- Direttiva del Presidente del Consiglio dei Ministri del 25 febbraio 2005, pubblicata nella Gazzetta Ufficiale n. 55 del 8 marzo 2005, "Ulteriori Indirizzi operativi per la gestione organizzativa e funzionale del sistema di allertamento nazionale, statale e regionale, per il rischio idrogeologico e idraulico ai fini di protezione civile, recanti modifiche ed integrazioni alla Direttiva del Presidente del Consiglio dei Ministri del 27 febbraio 2004";
- Indicazioni operative recanti "Metodi e criteri per l'omogeneizzazione dei messaggi del Sistema di allertamento nazionale per il rischio meteo-idrologico e idraulico e della risposta del sistema di protezione civile", impartite dal Capo Dipartimento della protezione civile, con nota prot. n. RIA/0007117 del 10 febbraio 2016.

Il Bollettino di criticità nazionale è emesso dal Centro Funzionale Centrale a seguito del recepimento delle criticità previste dai Centri Funzionali Decentrati delle Regioni o Province autonome competenti in materia nel proprio territorio. Le criticità vengono comunicate dai soggetti suddetti al Centro Funzionale Centrale utilizzando una Piattaforma informatica, ai cui "Termini e Condizioni" e "Disclaimer" si rimanda integralmente per quanto concerne l'utilizzo della Piattaforma stessa.

Il Bollettino di criticità nazionale è pubblicato dal Centro Funzionale Centrale di norma entro le ore 16,00 ora locale di ogni giorno, e contiene le previsioni di criticità e i livelli di allerta emessi dalle Regioni o Province autonome per il giorno corrente (di norma, dalle 16,00 alle 24,00) e per il giorno seguente (dalle 00,00 alle 24,00), per le zone d'allerta di loro competenza.

Le previsioni di criticità e i livelli di allerta contenuti nel Bollettino di criticità nazionale sono strumenti finalizzati al preannuncio in termini probabilistici, sulla base delle conoscenze disponibili, degli eventi e della conseguente evoluzione degli scenari di rischio al fine di attivare il Servizio nazionale della protezione civile ai diversi livelli territoriali.

martedì 24 novembre 2026

Il Dirigente

Firmato digitalmente da:
GIULIO FANCELLO
Firmato il 24/11/2026 15:20
Seriale Certificato: 008EAF1B
Valido dal 05/08/2026 al 05/08/2029

Ufficio II – Previsione e prevenzione del rischio